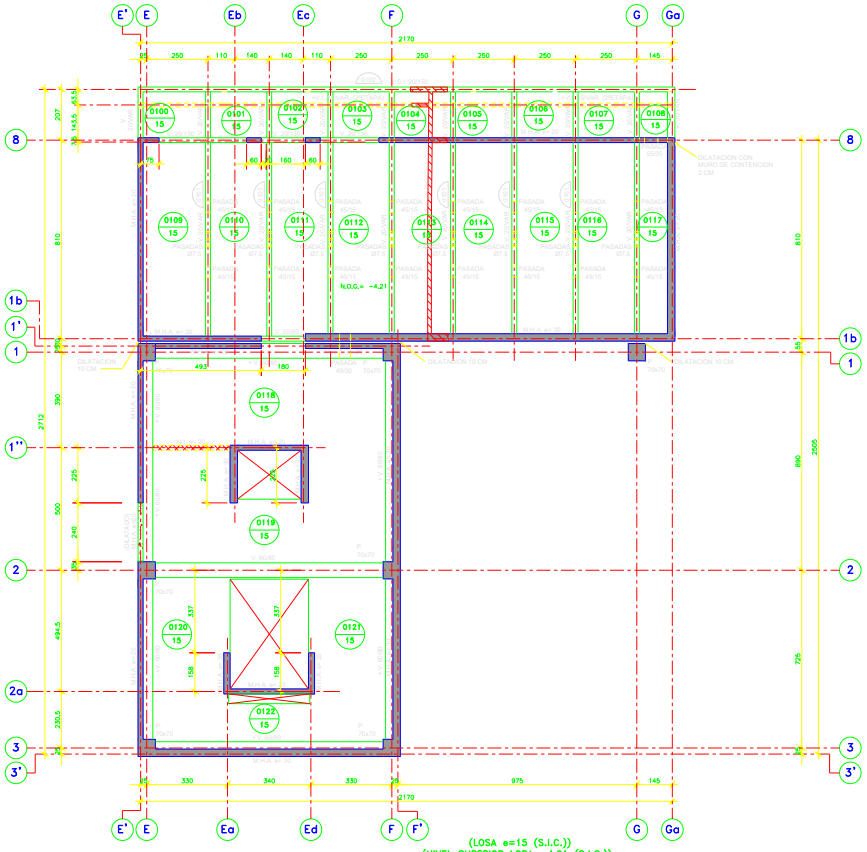
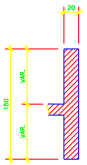


(LOSA e=15 (S.I.C.))
(NIVEL SUPERIOR LOSA -4.01 (S.I.C.))

PLANTA CIELO 1° SUBTERRANEO

ESCALA 1:75

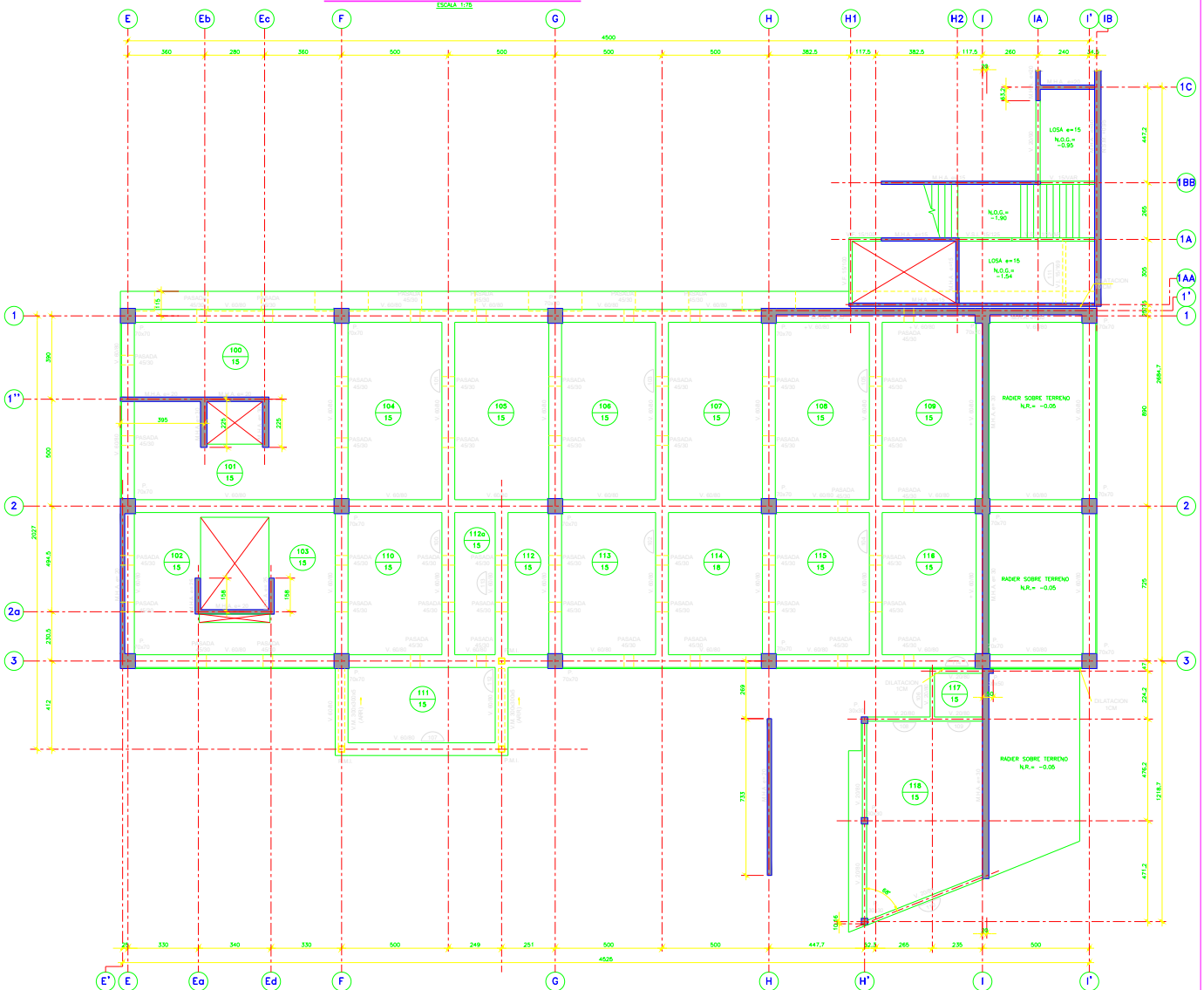


V.S.I. 20/150

ESCALA 1:25

CUADRO DE CONTRAFLECHAS	
LOSA	CONTRAFLECHA (cm.)
0100	–
0101	–
0102	–
0103	–
0104	–
0105	–
0106	–
0107	–
0108	–
0109	1.5
0110	1.5
0111	1.5
0112	1.5
0113	1.5
0114	1.5
0115	1.5
0116	1.5
0117	1.5
0118	0.5
0119	0.5
0120	–
0121	–
0122	–

CUADRO DE CONTRAFLECHAS	
LOSA	CONTRAFLECHA (cm.)
100	0.5
101	–
102	–
103	–
104	1
105	1
106	1
107	1
108	1
109	1
110	0.5
111	1
112	–
113	–
114	0.5
115	0.5
116	0.5
117	0.5



(LOSA e=15 (S.I.C.))
(NIVEL SUPERIOR LOSA -0.05)

PLANTA CIELO PISO 1°

ESCALA 1:75

2017-67-101 07/16pm Dec 11 Sec 2017

ESTADO: EN DESARROLLO | REVISADA | APROBADO PARA: PROPUESTA X | CONSTRUCCION

REV	DESCRIPCION	POR	FECHA
A			

PROYECTO: U. DE LOS ANDES
PLANTA CIELO 2° SUBTERRANEO
PLANTA CIELO 1° SUBTERRANEO

DISEÑO: | DIBUJO: | REVISO: | FECHA: | ESCALA: 1:75 | PLANO: 2017-67-101 | REV: A

MODELACION, Lo Prado 24, Of 1401, Las Condes
SANTIAGO, CHILE | FONO: +56 2 2264 0300
www.modelacion.com

rentalagos